문화는 일상을 움직이는 동력이다

걸어서 15분, 문화에 닿는 서울

: 보행일상권 관점에서 본 서울 문화 접근성 시각화

서울컬처헌터스

박주원
윤지영
조애림

목차

01 2040 서울 보행일상권, 왜 문화인가?
02 서울의 문화 활력 현황
03 문화 기반 인프라의 차이
04 시민이 실제로 누리는 문화시간
05 우리 동네 문화 프로필
06 왜 차이가 나는가? : 문화 부조화

2040 서울과 보행일상권, 왜 문화인가?

서울의 미래 비전: 문화로 완성되는 '보행일상권'

[그림 2-22] 보행일상권 개념도

2040 서울도시기본계획 7대 목표

- 2040 서울도시기본계획에서는 미래상인 '살기 좋은 나의 서울, 세계 속에 모두의 서울'을 도시공간에 구체화하기 위해서 아래 7개의 목표를 설정하였다.

[표 2-11] 2040 서울도시기본계획 7대 목표

구 분	7대 목표		주요 내용
어디서나 누릴 수 있는 "삶의 질"	1	걸어서 누리는 다양한 일상, '보행일상권 조성'	주거·일자리·여가문화·상업 등 다양한 일상생활을 도보 30분 내에서 향유
	2	수변 공간의 잠재력 발굴, '수변 중심 공간 재편'	물길의 잠재력을 이끌어내 지역과 시민생활 중심으로 재편
	3	새로운 도시공간의 창출, '기반시설 입체화'	도심 속 새로운 공간 창출을 위한 사람 중심의 기반시설 입체화 추진

보행일상권의 개념

- '보행일상권'이란 내가 사는 집을 중심으로 주거를 비롯한 업무·소비·여가·문화 등 다양한 활동을 도보 30분 내로 걸어서 누릴 수 있는 자족적인 생활권을 의미
- 디지털 대전환과 팬데믹으로 시공간의 제약이 사라지고 주거가 일상생활의 중심으로 부상하면서 달라진 시민 생활양식을 반영한 도시공간의 새로운 개념으로, 더 이상 멀리 이동하지 않고도 '나'의 생활반경 안에서 다양한 기능을 누릴 수 있도록 하는 것
- 기존에 수립한 116개 지역생활권을 기준으로 주거·상업·업무·여가문화 기능이 융복합하도록 재구성하여 자족적이고 탄소중립적이며 감염병에 안전한 새로운 서울형 생활권 단위를 의미

출처: 서울특별시 2040 서울도시 기본계획

2040 서울과 보행일상권, 왜 문화인가?

"문화시설·문화행사 = 지역 활성화 동력"

제328회 시의회 임시회
문화체육관광위원회

동행·매력 특별시 서울

SEOUL MY SOUL

주 요 업 무 보 고

2025. 2.

문 화 본 부

Ⅰ. 정책비전과 목표

비 전

시민과 함께하는 문화예술도시, 서울

추진목표

"문화와 예술이 일상이 되는"	"문화유산 미래가치를 창출하는"	"K컬처로 즐거움이 가득한"
문화 행복도시	2천년 역사도시	문화 매력도시

추진전략 및 과제

일상과 문화가 연결되는 문화예술 도시	문화유산의 보존 및 활용 강화	문화시설 확충 및 효율적인 시설 운영
○ 일상에서 만나는 시민문화 향유 기회 확대 ○ 문화매력도시 구현을 위한 예술 지원 강화	○ 지속가능한 문화유산 보존 관리 ○ 문화유산 활용 및 미래가치 제고	○ 서울 대표 박물관미술관 확충 및 운영 ○ 시민이 체감하는 문화시설 조성 및 운영

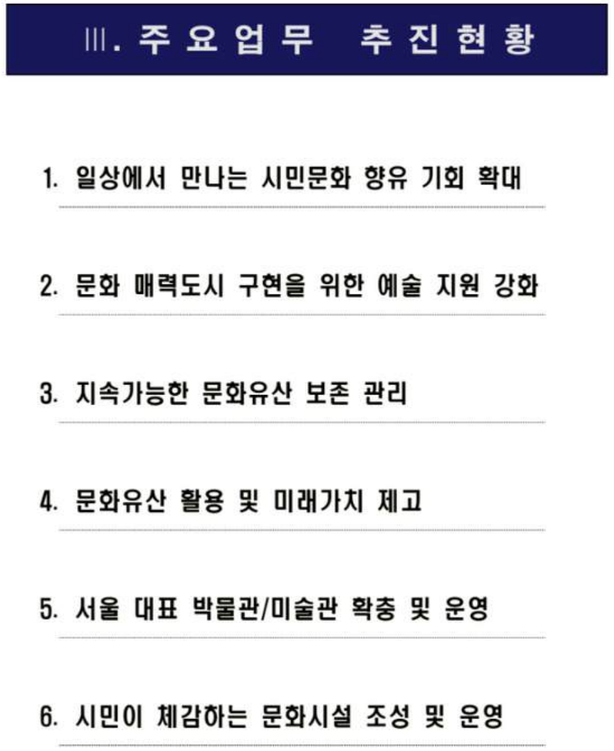

Ⅲ. 주요업무 추진현황

1. 일상에서 만나는 시민문화 향유 기회 확대
2. 문화 매력도시 구현을 위한 예술 지원 강화
3. 지속가능한 문화유산 보존 관리
4. 문화유산 활용 및 미래가치 제고
5. 서울 대표 박물관/미술관 확충 및 운영
6. 시민이 체감하는 문화시설 조성 및 운영

01

2040 서울과 보행일상권, 왜 문화인가?

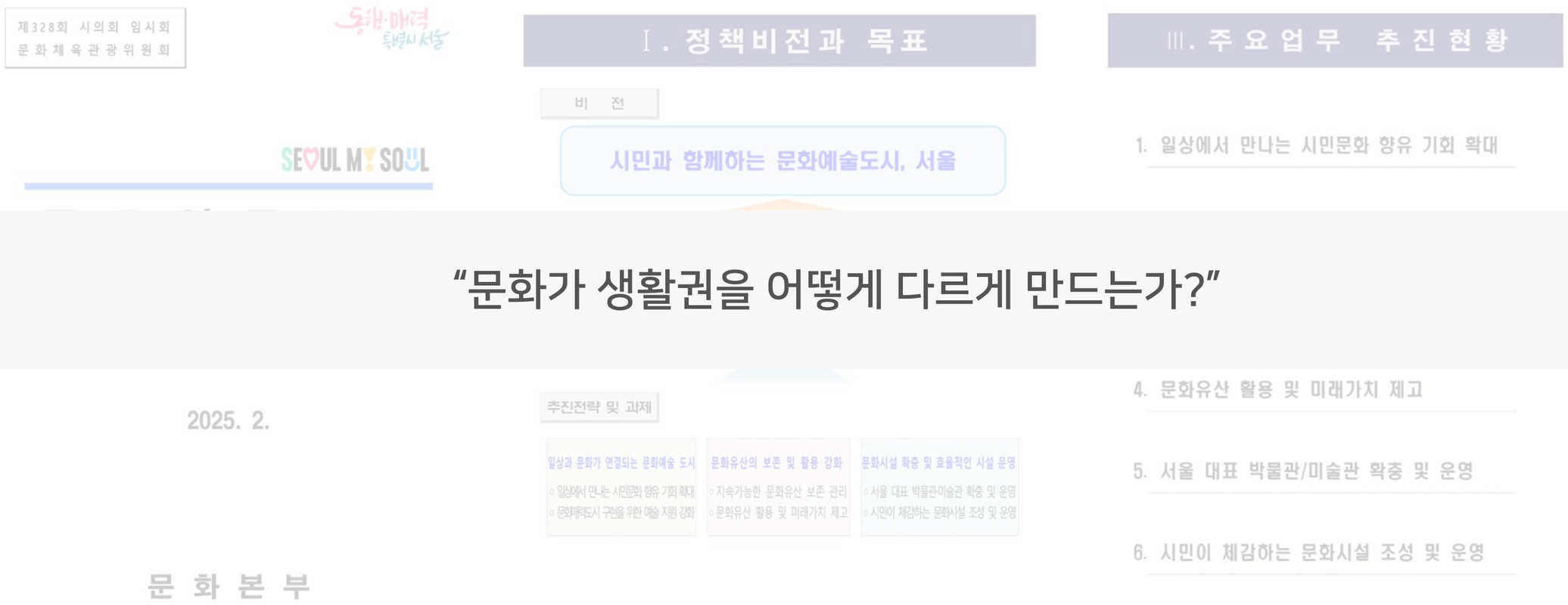

"문화가 생활권을 어떻게 다르게 만드는가?"

서울의 문화 활력 현황

52주 타임랩스 지도: “서울의 문화 맥박”

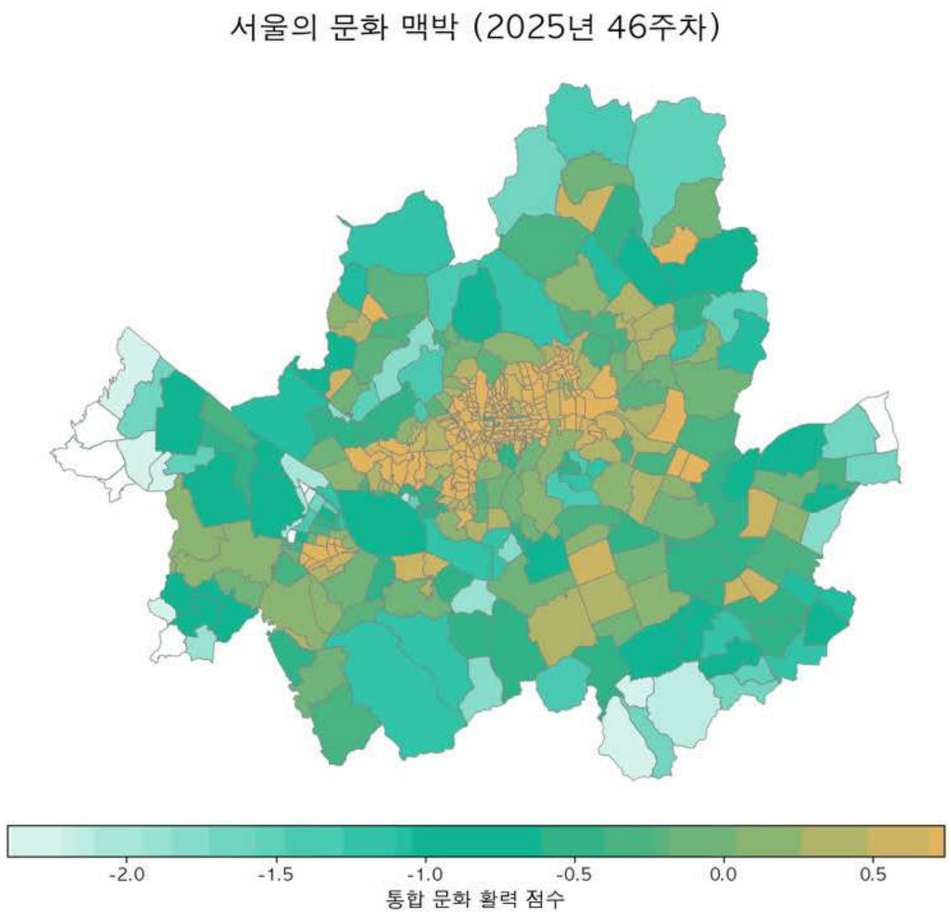

서울의 문화 활력 현황

DARK WEEKS 달력 : “언제, 어디가 소외되는가”

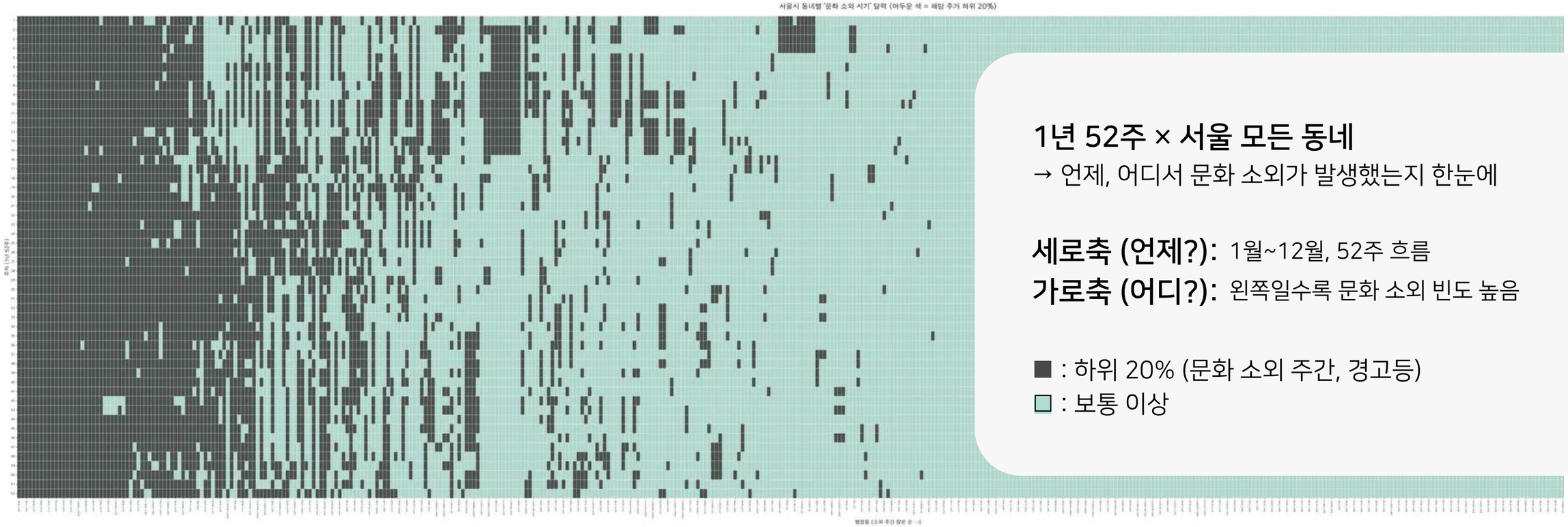

1년 52주 × 서울 모든 동네

→ 언제, 어디서 문화 소외가 발생했는지 한눈에

세로축 (언제?): 1월~12월, 52주 흐름

가로축 (어디?): 왼쪽일수록 문화 소외 빈도 높음

■ : 하위 20% (문화 소외 주간, 경고등)

□ : 보통 이상

서울의 문화 활력 현황

DARK WEEKS 달력 : “언제, 어디가 소외되는가”

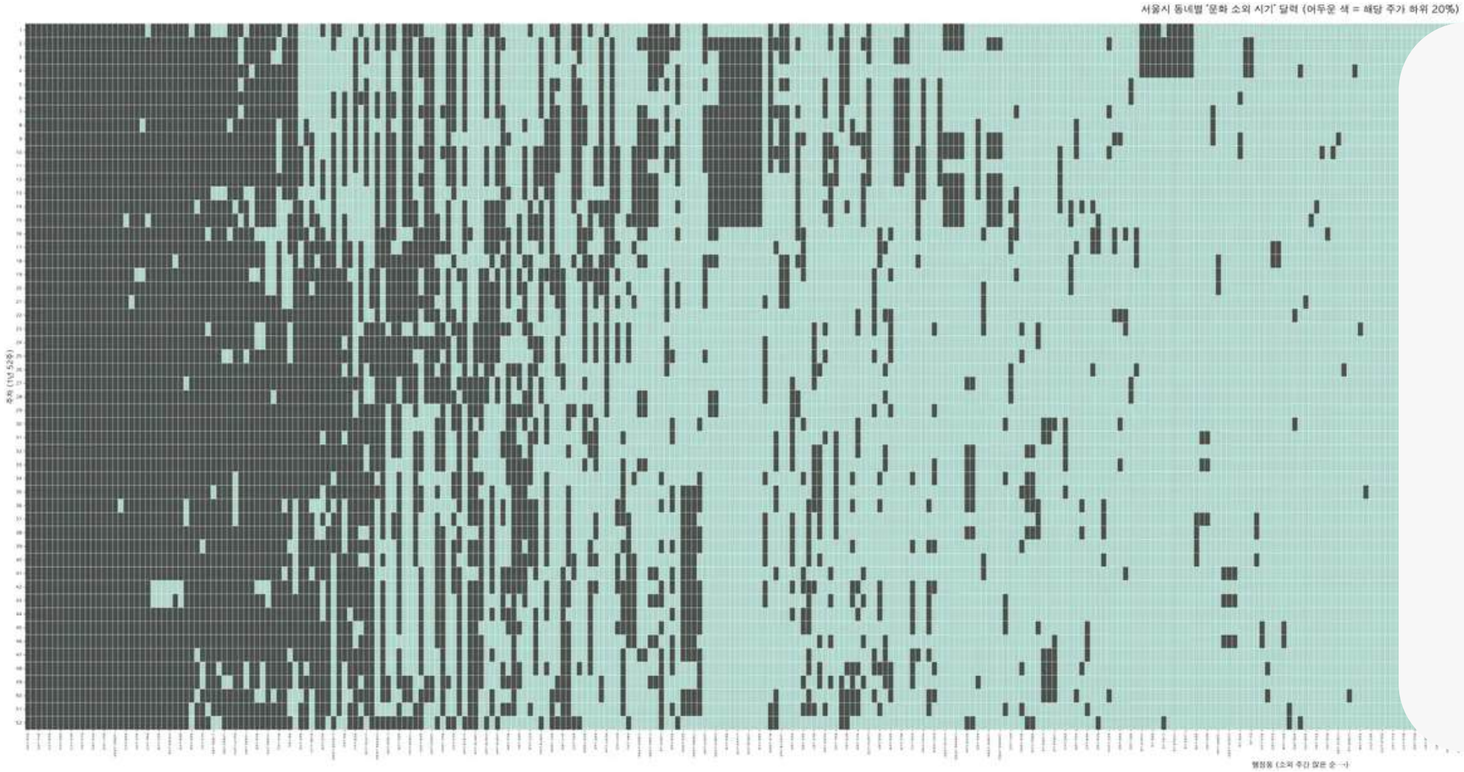

만성 소외

- 지역 검은색이 달력 위쪽에 집중
  → 특정 동네는 연중 꾸준히 소외

문화 비수기

- 연초(14주차), 늦여름(3335주차)에 파란색 확산

→ 서울 전체 문화활동 저조

동네별 맞춤 진단

- "우리 동네는 언제 부족한가?"
- 문화정책 맞춤형 대응 가능

문화 기반 인프라의 차이

서울시 동별 문화시설 접근성 현황 분석 (도보 15분 기준)

문화 인프라 히트맵: “시설이 많은 곳 VS 부족한 곳”

서울시 문화시설 커버리지 (도보 15분, % | 평균 85.9%)

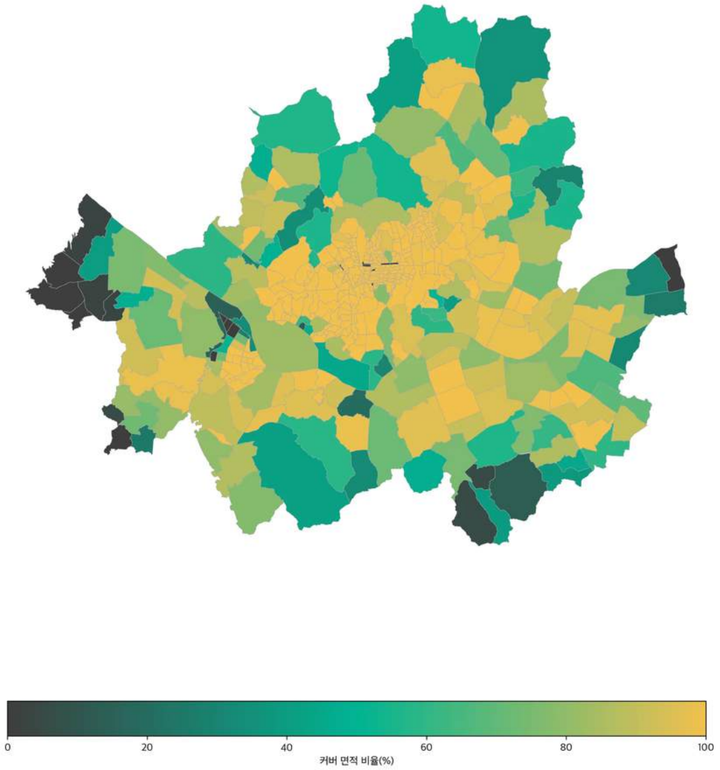

평균
: 85.9% (양호)
도심(종로·중구 등)
: 90~100% (거의 완벽)
외곽(서남권·동북권)
: 60% 이하, 일부 40% 미만

전체 평균은 높지만, 도심에 집중
→ **‘도넛형 불균형’**

동일한 서울 시민이라도 거주 지역에 따라 문화 격차 발생
→ **향후 정책은 소외 지역 인프라 집중 공급이 필요**

서울시 문화시설 커버리지 (등급화) (도보 15분, % | 평균 85.9%)

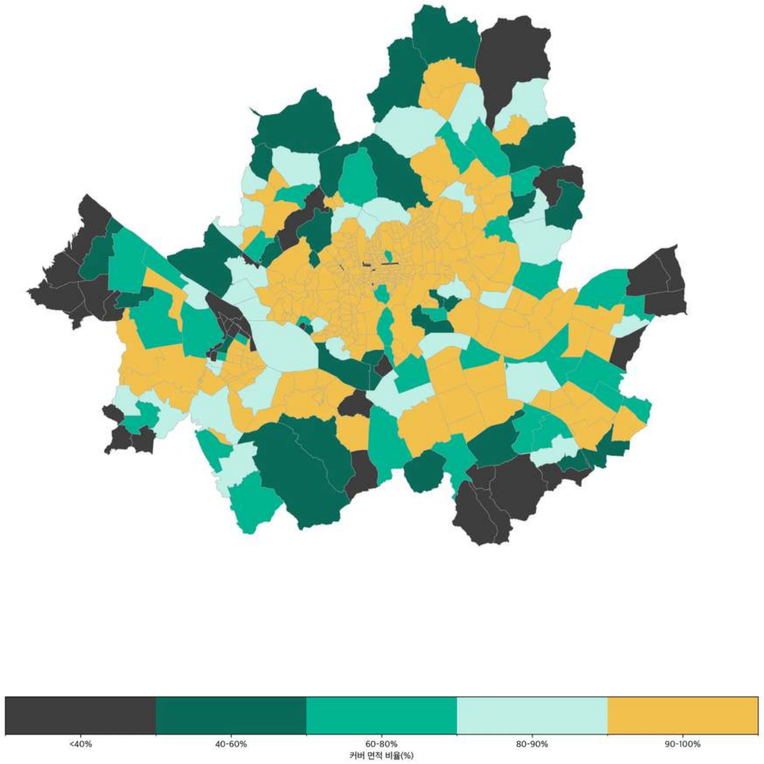

문화 기반 인프라의 차이

시설 다양성 지도(N_EFF): “많이 VS 다양하게”

서울시 문화시설 커버리지 (도보 15분, % | 평균 23.0%)

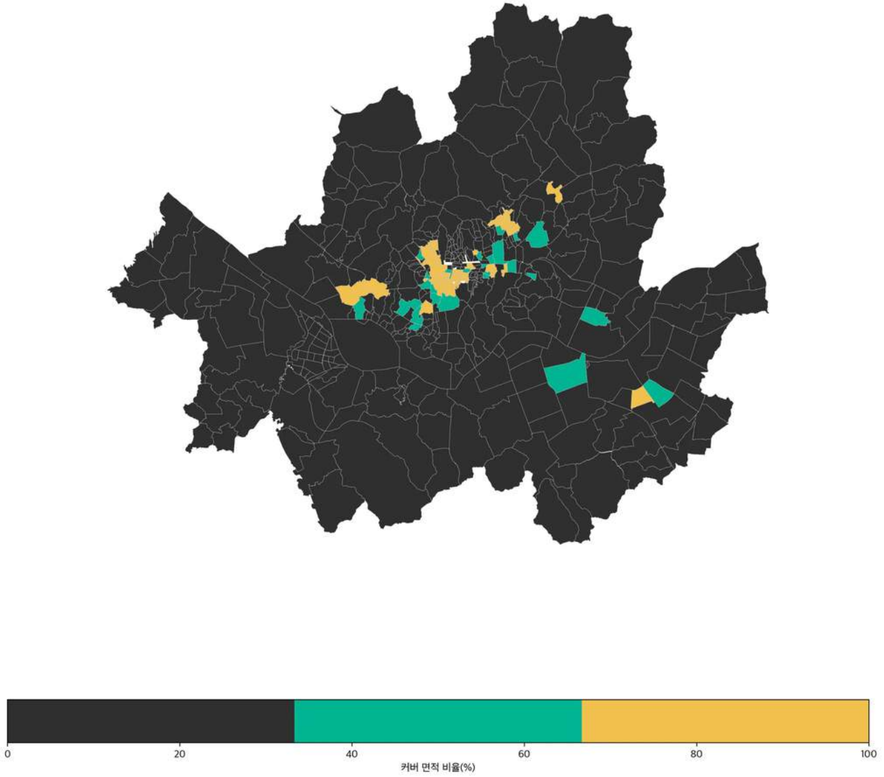

(우수, 67개 동)
: 동네 대부분(90% 이상)이
풍요로운 문화생활 가능

(양호, 35개 동)
: 동네 절반가량이 혜택을 보는
잠재력 지역

(개선필요, 356개 동)
: 다양성을 누릴 수 있는 곳이 거의 없는
소외 지역

문화 기반 인프라의 차이

시설 다양성 지도(N_EFF): “많이 VS 다양하게”

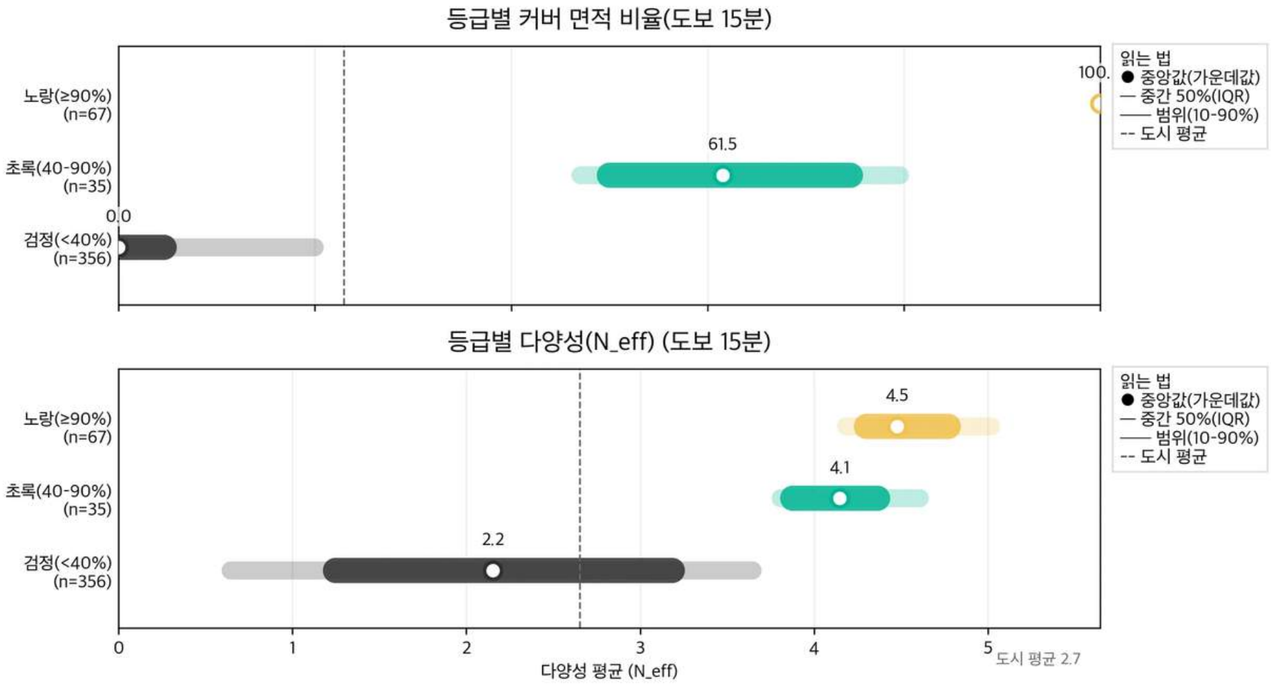

얼마나 넓게 가능한가? (커버 면적 비율)

- 🟡 : 동 면적의 90-100%가 혜택 범위
- 🟢 : 절반 이상 (중앙값 61.5%)
- ⚫ :혜택 지역 거의 없음 (중앙값 0%)

얼마나 다양하게 즐길 수 있나? (문화 종류)

- 🟡 : 4.5종의 시설을 균형있게 이용
- 🟢 : 4.1종으로 양호한 수준
- ⚫ : 2.2종에 불과, 선택권 매우 제한적

문화 기반 인프라의 차이

시설 다양성 지도(N_EFF): 문화시설 구성비 분석 N_EFF

체부동 — N_eff 5.3 · 커버 100.0% (도보 15분)

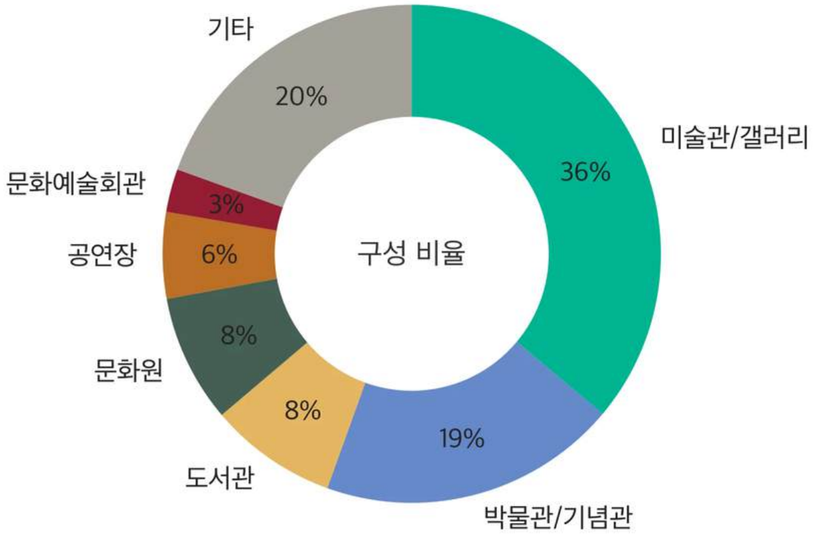

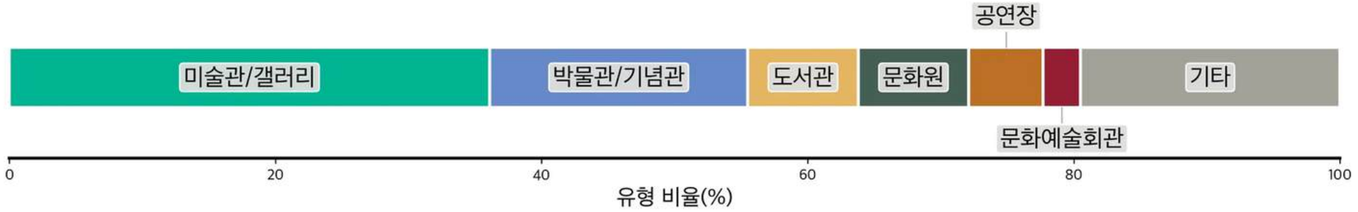

문화 기반 인프라의 차이

2X2 매트릭스 산점도

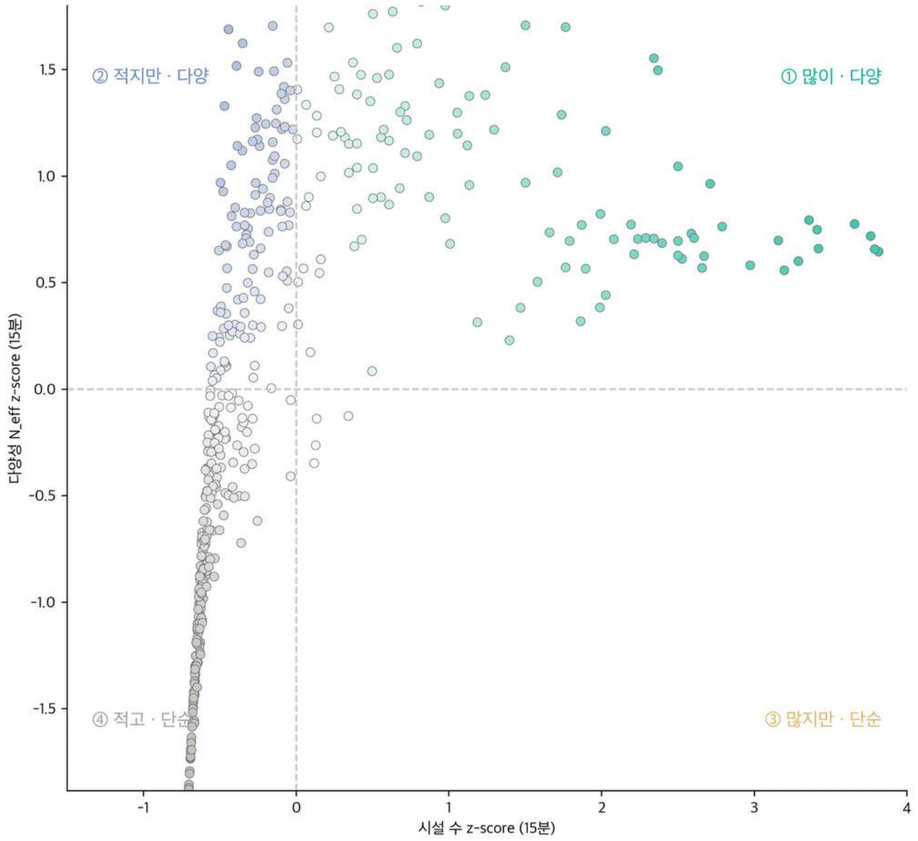

문화 기반 인프라의 차이

시간대 스몰 멀티플(10분, 15분,30분)

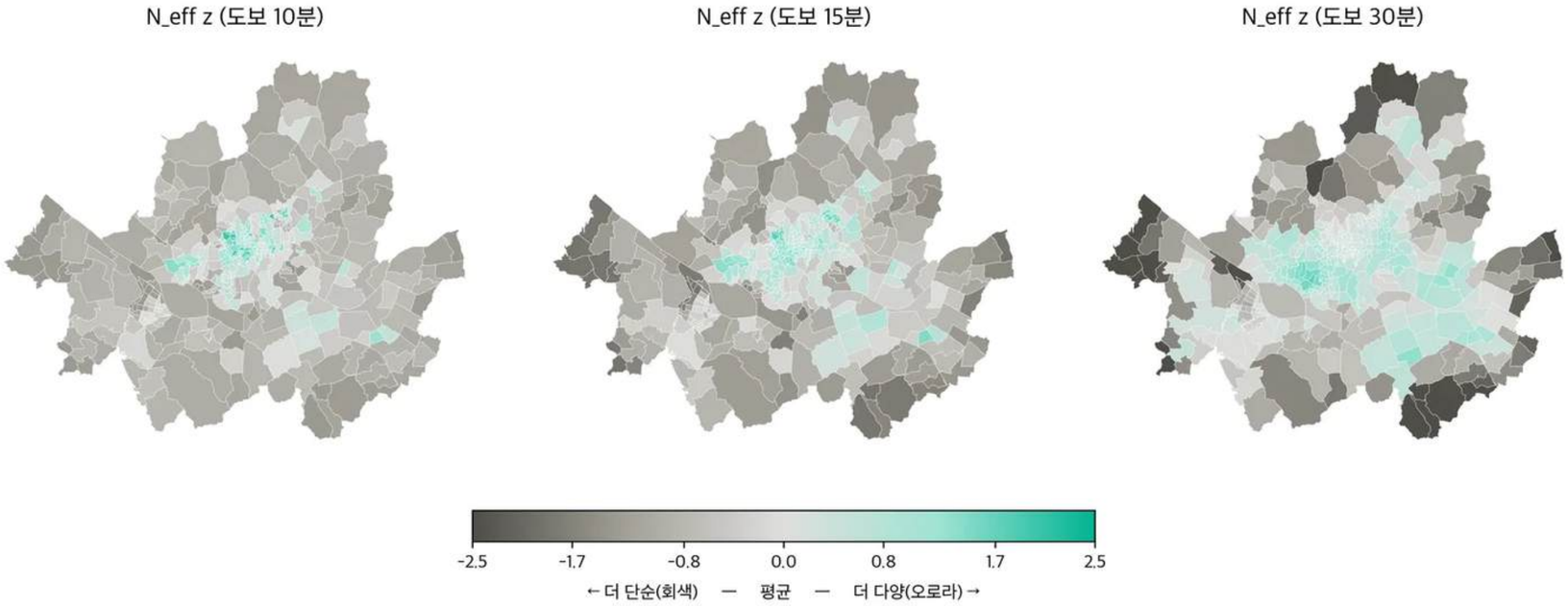

문화 기반 인프라의 차이

보행 환경 지수 소형 패널

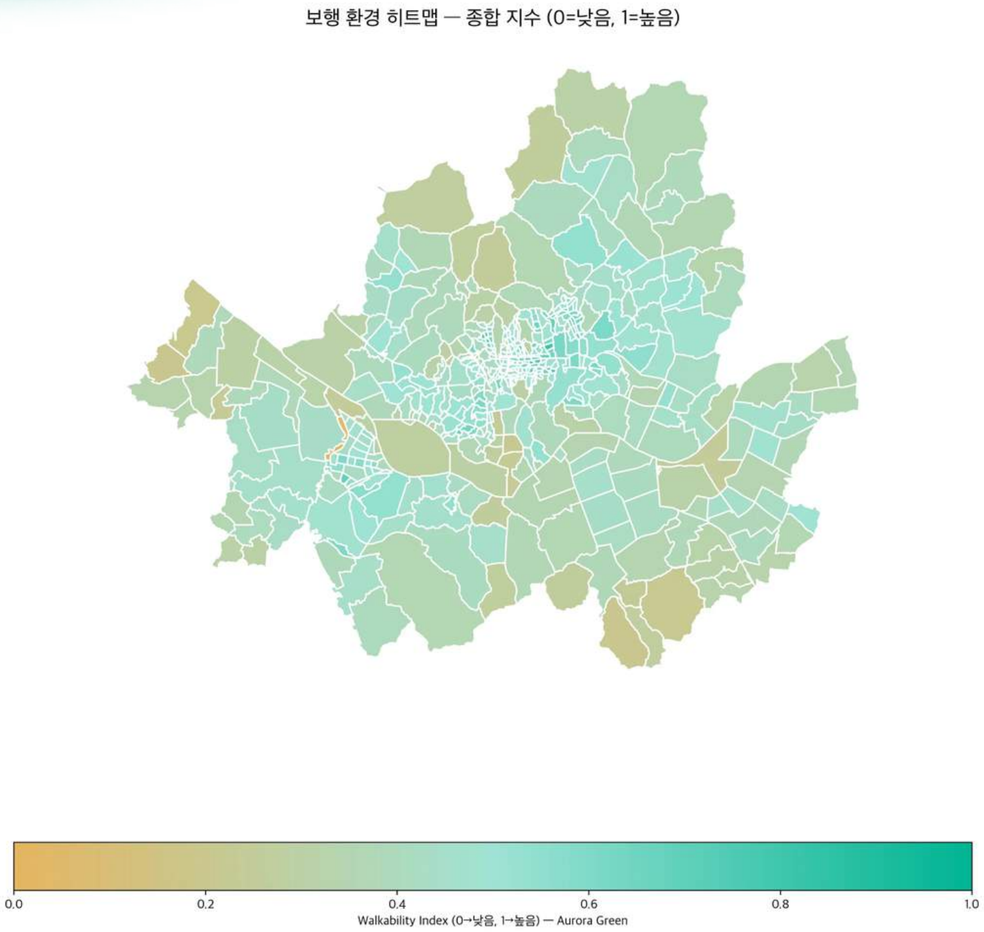

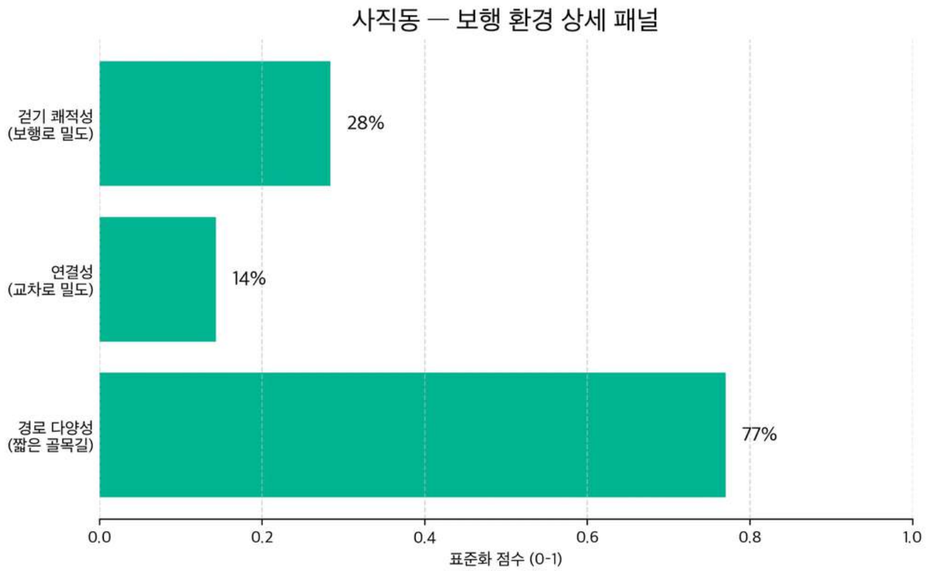

문화 기반 인프라의 차이

보행 환경 & TOP/BOTTOM 비교

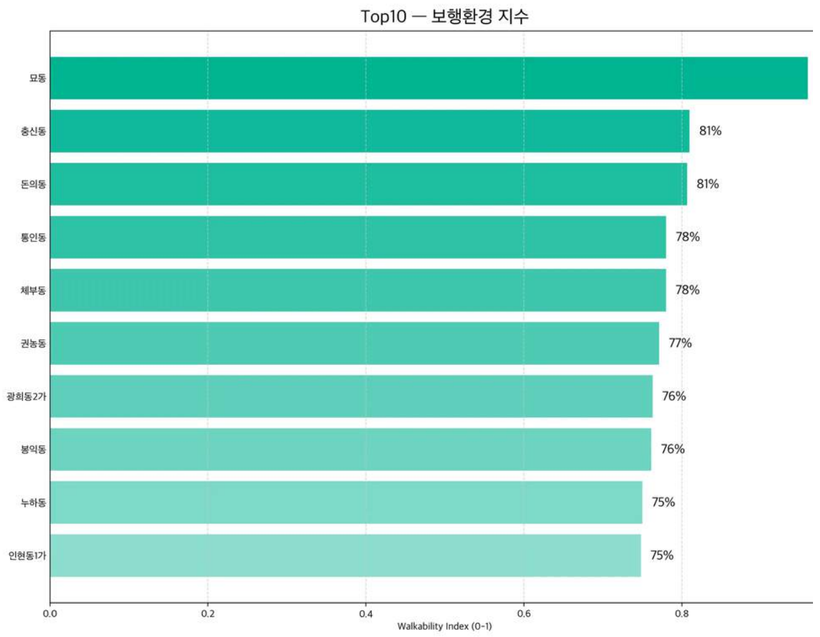

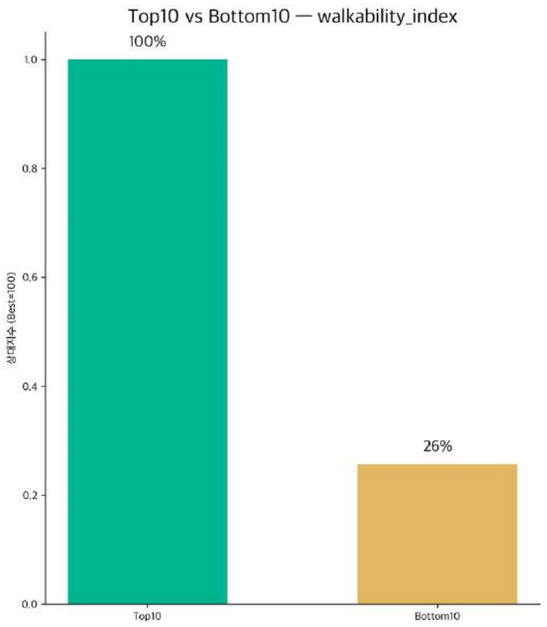

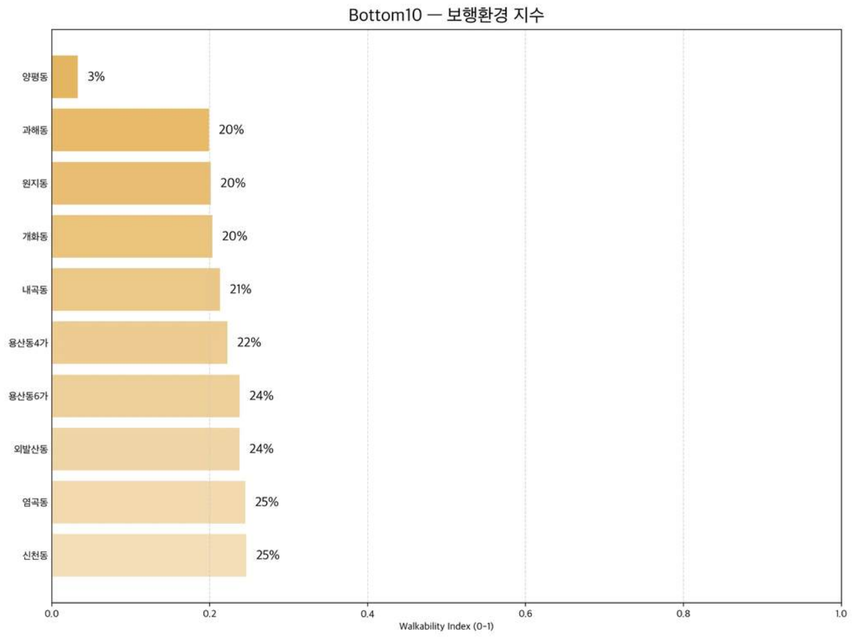

시민이 실제로 누리는 문화시간

AFTER-WORK ECOH 지도 : 퇴근 후, 나에게 남은 문화시간은?

서울시 동네별 '퇴근 후 문화생활' 가능 시간 (ECOH) — 시설만, 면적 커버리지 기반

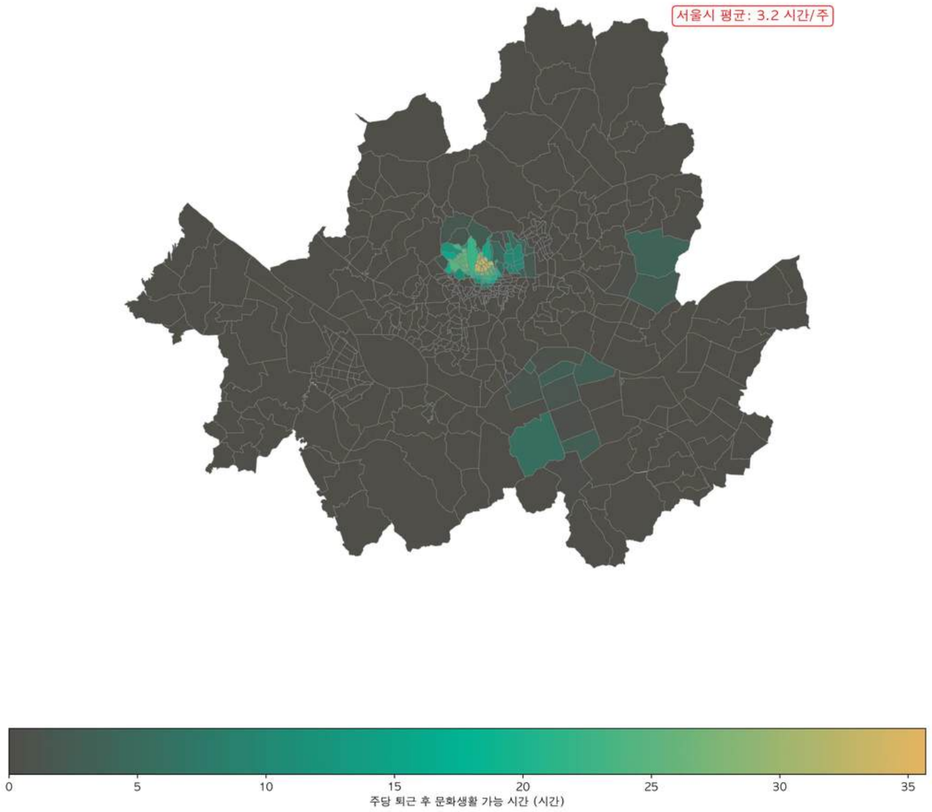

"열려 있어야 진짜 접근이다"

우리 동네 문화 프로필

A/B/C/D 네 가지 유형으로 보는 서울의 문화 얼굴

B : 팝업 성지

A: 꾸준한 활력

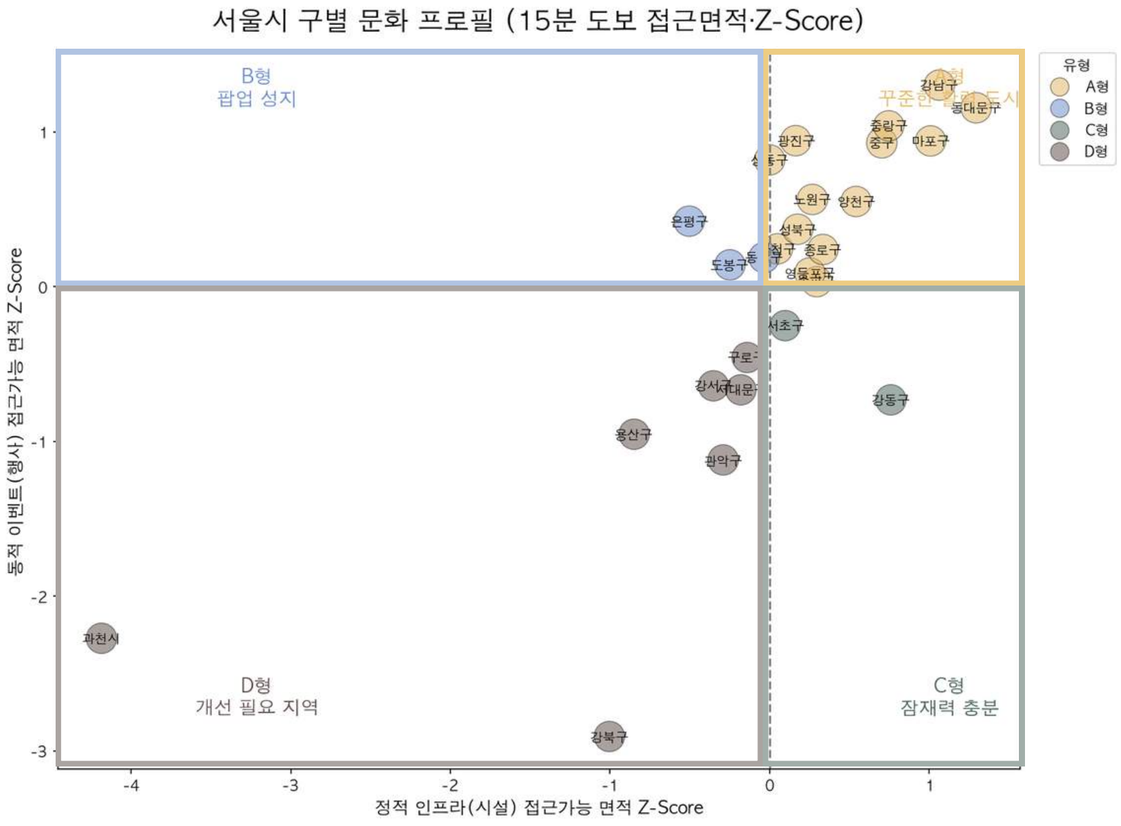

D : 개선 필요

C : 잠재력 충분

결론 및 정책 제안

“문화는 생활권 활성화의 핵심 인프라”

1. 소외 지역·시기 집중 지원
2. 퇴근 후 운영시간 확대
3. 보행 네트워크 개선